PIB TRAJET

Date et Heure de production (UTC)	Date et heure de départ (UTC)	Durée
29-03-2026 20:13	30-03-2026 10:00	0400
Règle de vol	**Départ**	**Destination**
VFR	LFBX	LFBD
Plancher (en FL)	**Plafond (en FL)**	**Rayon (en NM)**
0	055	30
Demi-couloir (en NM)		
15		

AÉRODROME DE DÉPART

LFBX PERIGUEUX BASSILLAC

INSTALLATIONS ET SERVICES

LFFA-D6629/25
DU: 21 11 2025 09:17 AU: 01 05 2026 00:00
A)LFBX
Q) LFBB / QFAAR / IV / NBO / A / 000/999 / 4512N00049E005
E) VOLS COMMERCIAUX ET TOUS VOLS MTOW SUPERIEURE A 1.9T : DEMANDE OBLIGATOIRE PAR MYHANDLING.

LFFA-D1671/26
DU: 26 03 2026 13:18 AU: 30 04 2026 15:00
A)LFBX
Q) LFBB / QFAXX / IV / NBO / A / 000/999 / 4512N00049E005
E) SPPA INDISPONIBLE

LFFA-D1667/26
DU: 30 03 2026 06:00 AU: 31 03 2026 15:00
A)LFBX
Q) LFBB / QFFAH / IV / BO / A / 000/999 / 4512N00049E005
E) HORAIRES ET NIVEAUX RFFS :
- NIVEAU 1 : 0600-1000 1100-1500
- EN DEHORS DE CES HORAIRES, NIVEAU 5 DISPONIBLE POUR :
. VOLS COMMERCIAUX PPR 48HR PAR MAIL : PERIGUEUX.AFIS(AT)EDEIS.COM
. VOLS MEDEVAC PPR 02RH PAR TEL : 06 08 82 98 68

LFFA-D6160/25
DU: 24 10 2025 06:31 AU: 01 05 2026 00:00
A)LFBX
Q) LFBB / QFULT / IV / NBO / A / 000/999 / 4512N00049E005
E) AVITAILLEMENT JET A1 : PAIEMENT PAR CARTE BANCAIRE ET CARTES 'BROKERS'.

LFFA-D6161/25
DU: 24 10 2025 06:33 AU: 01 05 2026 00:00
A)LFBX
Q) LFBB / QFULT / IV / NBO / A / 000/999 / 4512N00049E005
E) AVITAILLEMENT AUTOMATE AVGAS : PAIEMENT PAR CARTE BANCAIRE ET BADGES 'EDEIS'.

LFFA-D1668/26
DU: 30 03 2026 06:00 AU: 31 03 2026 15:00
A)LFBX
Q) LFBB / QFUAP / IV / NBO / A / 000/999 / 4512N00049E005
E) AVITAILLEMENT JET A1 DISPONIBLE UNIQUEMENT SUR PPR 02HR PAR TEL :
06 08 82 98 68.

AIRE DE MANŒUVRE

LFFA-D1558/26
DU: 20 03 2026 12:30 AU: 17 04 2026 15:00
A)LFBX
Q) LFBB / QMRLC / IV / NBO / A / 000/999 / 4512N00049E005

E) PISTE NON REVETUE 11L/29R FERMEE

AIRE DE TRAFIC

LFFA-D1559/26
DU: 20 03 2026 12:37 AU: 23 09 2026 00:00
A)LFBX
Q) LFBB / QMPLC / IV / BO / A / 000/999 / 4512N00049E005
E) PARKING EST : PREMIER POSTE DE STATIONNEMENT INUTILISABLE.

ORGANISATION DE L'ESPACE AÉRIEN ET SERVICES DE LA CIRCULATION AÉRIENNE

LFFA-D1670/26
DU: 30 03 2026 06:00 AU: 31 03 2026 15:00
A)LFBX
Q) LFBB / QSFAR / IV / BO / A / 000/999 / 4512N00049E005
E) AFIS DISPONIBLE VOLS COMMERCIAUX PPR 48HR PAR MAIL :
PERIGUEUX.AFIS(A)EDEIS.COM
AFIS DISPONIBLE VOLS MEDEVAC PPR 2H PAR TEL : 06 08 82 98 68

AÉRODROME DE DESTINATION

LFBD BORDEAUX MERIGNAC

INSTALLATIONS ET SERVICES

LFFA-A1752/26
DU: 30 03 2026 05:00 AU: 31 03 2026 10:30
A)LFBD
Q) LFBB / QFALT / IV / NBO / A / 000/999 / 4450N00043W005
E) RESTRICTIONS UTILISATION AERODROME :
AD NE PEUT ETRE CHOISI COMME AERODROME DE DEGAGEMENT POUR DES
AERONEFS D'ENVERGURE SUPERIEURE A 36M, SAUF AERONEFS MILITAIRES
A DESTINATION DE L'AIRE DE STATIONNEMENT MILITAIRE.

LFFA-M0734/26
DU: 05 03 2026 13:27 AU: 01 07 2026 16:00
A)LFBD
Q) LFBB / QFALT / IV / NBO / A / 000/999 / 4450N00043W005
E) VOLS MILITAIRES A DESTINATION DE LA BA106 CONTACTER 'MERIGNAC OPS'
SUR 140.275MHZ 15MINUTES AVANT L'ATTERRISSAGE.
POUR TOUTES INFORMATIONS, CONTACTER LE BUREAU OPERATION BASE AU
05 33 89 81 05 OU 865 106 81 05.

LFFA-A1467/26
DU: 16 03 2026 17:00 AU: 17 04 2026 17:00
A)LFBD
Q) LFBB / QFAHW / IV / BO / A / 000/999 / 4450N00043W005
E) SUP AIP 143/25 - PHASES 3B ET 3C ACTIVES

LFFA-A1549/26
DU: 13 03 2026 09:48 AU: 29 05 2026 23:59
A)LFBD
Q) LFBB / QFATT / IV / BO / A / 000/999 / 4450N00043W005
E) NOTAM TRIGGER - SUP AIP AIRAC 143/25 MODIFIE :
TRAVAUX DE REFONTE DES POSTES DE STATIONNEMENT DU PARKING 'BRAVO'.
LES DATES DE DEBUT ET DE FIN DE PHASE SERONT CONFIRMEES PAR NOTAM.
LES DISPOSITIONS CONTENUES DANS CE SUP AIP SONT PROROGEES JUSQU'AU 29 MAI 2026.
CE SUP AIP EST DISPONIBLE SUR WWW.SIA.AVIATION-CIVILE.GOUV.FR

AIRE DE MANŒUVRE

LFFA-A1354/26
DU: 05 03 2026 15:37 AU: PERM
A)LFBD
Q) LFBB / QMRXX / IV / NBO / A / 000/999 / 4450N00043W005
E) SUPPRESSION DES VALEURS DE TDZ PISTES 23 ET 29 :

REF AIP AD 2 LFBD.12.

LFFA-A1797/26
DU: 30 03 2026 11:00 AU: 30 03 2026 16:00
A)LFBD
Q) LFBB / QMRLC / IV / NBO / A / 000/999 / 4450N00043W005
E) PISTE 11/29 FERMEE POUR TRAVAUX SAUF ROULAGE COTE SEUIL 29

LFFA-A0490/26
DU: 01 02 2026 00:00 AU: PERM
A)LFBD
Q) LFBB / QMAXX / IV / NBO / A / 000/999 / 4450N00043W005
E) PARTIES DE L'AIRE DE MOUVEMENT UTILISABLES PAR A400 :
- RWY 11/29
- TWY G, S4, F
REF AIP AD 2 LFBD.20, AD 2 LFBD.21.

LFFA-A0491/26
DU: 19 02 2026 00:00 AU: PERM
A)LFBD
Q) LFBB / QMTXX / IV / NBO / A / 000/999 / 4450N00043W005
E) ALTITUDES THR MODIFIEES :
- THR 05 : 160 FT.
- THR 23 : 151 FT.
- THR 11 : 153 FT.
- THR 29 : 160 FT.
REF AIP AD 1.3, AD 2 LFBD.12.

LFFA-A1798/26
DU: 30 03 2026 11:00 AU: 30 03 2026 16:00
A)LFBD
Q) LFBB / QMXLC / IV / BO / A / 000/999 / 4450N00043W005
E) TAXIWAY S4 FERME CAUSE TRAVAUX.

AIRE DE TRAFIC

LFFA-A1751/26
DU: 30 03 2026 05:00 AU: 31 03 2026 16:00
A)LFBD
Q) LFBB / QMPLC / IV / BO / A / 000/999 / 4450N00043W005
E) POSTE AVION Y13 FERME

LFFA-A1860/26
DU: 30 03 2026 06:30 AU: 03 04 2026 15:00
A)LFBD
Q) LFBB / QMPLC / IV / BO / A / 000/999 / 4450N00043W005
E) POSTE AVION D1 FERME POUR TRAVAUX.

RESTRICTIONS DE L'ESPACE AÉRIEN

LFFA-R1979/25
DU: 04 09 2025 00:00 AU: 15 04 2026 23:59
A)LFBD
Q) LFBB / QRTTT / IV / BO / AW / 000/035 / 4450N00051W006
E) NOTAM TRIGGER - SUP AIP 148/25 :
ACTIVITES SPECIFIQUES DEFENSE NECESSITANT LA CREATION DE 4 ZONES REGLEMENTEES TEMPORAIRES (ZRT)
DANS LA CTR BORDEAUX MERIGNAC.
UNE PARTIE DE LA ZRT 247A (2000FT/3500FT AMSL) EST ACTIVABLE PAR
NOTAM.
CE SUP AIP EST DISPONIBLE SUR WWW.SIA.AVIATION-CIVILE.GOUV.FR
F) SFC
G) 3500FT AMSL

OBSTACLES

LFFA-P0787/26

DU: 04 03 2026 06:00 AU: 31 03 2026 16:00
A)LFBD
Q) LFBB / QOBCE / IV / M / A / 000/999 / 4450N00043W005
E) GRUES MOBILES - PARKING P4 - MERIGNAC :
- PSN : 444939.7N 0004121.4W
- RDL 093/1.11NM ARP LFBD 'BORDEAUX MERIGNAC'
- HAUTEUR : 77FT
- ALT AU SOMMET : 228FT
- BALISAGE : JOUR ET NUIT.

LFFA-P1104/26
DU: 29 03 2026 06:00 AU: 10 04 2026 16:00
A)LFBD
Q) LFBB / QOBCE / IV / M / A / 000/999 / 4450N00043W005
D) 0600-1600
E) GRUE MOBILE ERIGEE A 'MERIGNAC' - RDL 061/0.82NM ARP LFBD :
- PSN : 445006.51N 0004154.42W
- HAUTEUR : 92FT
- ALTITUDE AU SOMMET : 247FT
- BALISAGE : JOUR.

LFFA-P1106/26
DU: 29 03 2026 06:00 AU: 10 04 2026 16:00
A)LFBD
Q) LFBB / QOBCE / IV / M / A / 000/999 / 4450N00043W005
D) 0600-1600
E) GRUE MOBILE A MERIGNAC AD - RDL061/0.82NM ARP LFBD
PSN:445006N 0004154W
HAUTEUR: 82FT
ALT SOMMET: 236FT
BALISAGE: JOUR

LFFA-P1166/26
DU: 30 03 2026 05:00 AU: 30 04 2026 16:00
A)LFBD
Q) LFBB / QOBCE / IV / M / A / 000/999 / 4450N00043W005
D) 0500-1600
E) GRUE MOBILE A MERIGNAC RDL 060/1.45NM ARP LFBD :
- PSN : 445026.17N 0004108.29W
- HAUTEUR : 147FT
- ALT AU SOMMET : 295FT
- BALISAGE : JOUR ET NUIT

EN-ROUTE

ORGANISATION DE L'ESPACE AÉRIEN ET PROCÉDURES

LFBB FIR BORDEAUX

LFFA-F0315/26
DU: 22 02 2026 10:33 AU: 21 05 2026 23:59
A)LFBB
Q) LFBB / QAFHX / IV / NBO / E / 000/030 / 4432N00108W025
E) MIGRATION DE CIGOGNES ET DE VANNEAUX HUPPES :
-PSN : 443206N 0010753W
-LIMITES VERTICALES : SFC A 3000FT AMSL
-FLUX SUD VERS LE NORD.

LFBC CAZAUX

LFFA-M1019/26
DU: 30 03 2026 09:15 AU: 03 04 2026 10:15
A)LFBC

Q) LFBB / QPFCA / IV / NBO / AE / 000/999 / 4439N00128W058
D) 0915-1015
E) REGULATION POUR TRAFIC MILITAIRE :
- RECUEIL DE 3 AIRCRAFT TOUTES LES 15MIN MAX.
- ZONES CONCERNEES : LFR31 (A1, A2, A3, A4, A5, A6 ,A7, H), CTR CAZAUX, TMA (1, 2, 3, 4, 5 ET 6).

LFBL LIMOGES BELLEGARDE

LFFA-A0416/26
DU: 20 01 2026 14:39 AU: PERM
A)LFBL
Q) LFBB / QATCA / IV / NBO / AE / 000/145 / 4556N00133E076
E) HOR ATS : DU LUN 0515 AU SAM 2200
AUTRES JOURS SANS CHANGEMENT
REF AD2 LFBL.3
AD2 LFBL TXT 03

LFBE BERGERAC DORDOGNE PERIGORD

LFFA-B1042/26
DU: 30 03 2026 00:00 AU: 12 04 2026 23:00
A)LFBE
Q) LFBB / QACAH / IV / BO / AE / 000/020 / 4449N00031E009
E) HORAIRES ACTIVITE CTR BERGERAC :
- LUN-VEN : 0600-1800
- SAM : 0630-1015 1130-1530
- DIM : 0700-1015 1130-1600
- EXTENSION POSSIBLE DE 1HR POUR VOLS COMMERCIAUX PROGRAMMES
- EN DEHORS DE CES HORAIRES CTR DECLASSEE EN G ET CTL AD NON ASSURE.

LFSL BRIVE SOUILLAC

LFFA-B1260/26
DU: 30 03 2026 00:00 AU: 05 04 2026 23:59
A)LFSL
Q) LFBB / QACAH / IV / BO / AE / 000/025 / 4502N00130E007
E) HORAIRES ACTIVITE CTR BRIVE :
LUN-MAR : 0430-1630 1745-1930
MER : 1100-1630 1745-1930
JEU-VEN : 0430-1630 1745-1930
SAM : 0800-1015 1130-1600
DIM : 1200-1630 1745-1930.

LFBB FIR BORDEAUX - LFEE FIR REIMS - LFFF FIR PARIS FIR - LFMM FIR MARSEILLE - LFRR FIR BREST

LFFA-F0627/25
DU: 01 05 2025 00:00 AU: PERM
A)LFBB LFEE LFFF LFMM LFRR
Q) LFXX / QPRCH / IV / BO / E / 000/999 / 4412N00040E460
E) APPLICATION DE LA NOUVELLE REGLEMENTATION EUROPEENNE IR SERA 2024/404 EN VIGUEUR LE 1ER MAI 2025 AVEC L'INTRODUCTION DU POINT SERA.14083 RELATIF AUX PROCEDURES EN CAS DE PANNE DE COMMUNICATION RADIO.
MODIFICATION DE LA PROCEDURE PANNE RADIO : INTRODUCTION DU NOUVEAU CODE D'URGENCE 7601 ET MODIFICATION DE LA REGLE DES 7MIN EN 20MIN.
REF AIP ENR1.1

SERVICES DE LA CIRCULATION AÉRIENNE ET VOLMET

LFRR FIR BREST - LFFF FIR PARIS FIR - LFEE FIR REIMS - LFBB FIR BORDEAUX

LFFA-F1418/25
DU: 10 10 2025 00:00 AU: PERM
A)LFRR LFFF LFEE LFBB
Q) LFXX / QSCXX / IV / NBO / E / 000/999 / 4912N00005E325
E) EN RAISON D'UNE MISE A JOUR TECHNIQUE, CERTAINS NUMEROS DE
TELEPHONES DU CENTRE DE DETECTION ET DE CONTROLE (CDC) DE
CINQ-MARS-LA-PILE VONT CHANGER.
SEULS LES NUMEROS SUIVANTS DOIVENT ETRE UTILISES:
CSCAM: 02.45.34.16.02 (862 927 1602)
BIV: 02.45.34.16.03 (862 927 1603)
MC: 02.45.34.16.05 (862 927 1605) ET 02.45.34.16.06 (862 927 1606)
TPO: 02.45.34.16.09 (862 927 1609)
OMC: 02.45.34.16.10 (862 927 1610)
FA: 02.45.34.16.11 (862 927 1611)
CHEF OPS: 02.45.34.14.00 (862 927 1400)
CDC CINQ MARS LA PILE POC : 02 45 34 28 63

GNSS - INSTALLATIONS DE RADIONAVIGATION

LFBG COGNAC CHATEAUBERNARD

LFFA-F0558/26
DU: 30 03 2026 11:30 AU: 30 03 2026 12:00
A)LFBG
Q) LFBB / QNNAS / IV / BO / AE / 000/999 / 4540N00018W025
E) TACAN CGC 116.200MHZ/CH109X HORS SERVICE

RESTRICTIONS DE L'ESPACE AÉRIEN

LFBC CAZAUX

LFFA-R3138/25
DU: 16 12 2025 10:30 AU: PERM
A)LFBC
Q) LFBB / QRPCH / IV / NBO / AW / 000/012 / 4432N00107W003
E) LF-P200L: CONTACT MODIFIE:
LIRE : BA120-OPS.CDU.FCT(A)INTRADEF.GOUV.FR
A LA PLACE DE : BA120-GAA.CDT.FCT(A)INTRADEF.GOUV.FR
REF AIP FRANCE ENR 5.1
F) SFC
G) 500FT AGL

LFBB FIR BORDEAUX - LFMM FIR MARSEILLE

LFFA-R0966/26
DU: 30 03 2026 07:30 AU: 30 03 2026 14:00
A)LFBB LFMM
Q) LFXX / QRRCA / IV / BO / W / 042/195 / 4531N00214E048
D) 0730-0830 1100-1215 1300-1400
E) LF-R68 A B C ACTIVES.
F) 4200FT AMSL
G) FL195

LFBB FIR BORDEAUX

LFFA-R0629/26
DU: 23 03 2026 05:00 AU: 01 04 2026 04:00
A)LFBB

Q) LFBB / QRRCA / IV / BO / W / 000/030 / 4511N00021W002
E) ZONE REGLEMENTEE LF-R249 'CAMP DE BUSSAC' ACTIVE
F) SFC
G) 3000FT AMSL

LFRR FIR BREST - LFBB FIR BORDEAUX

LFFA-R3154/25
DU: 22 01 2026 00:00 AU: 21 01 2027 23:59
A)LFRR LFBB
Q) LFXX / QRTTT / IV / BO / W / 000/999 / 4551N00432W190
E) NOTAM TRIGGER - SUP AIP AIRAC 207/25 MODIFIE :
TIRS DE MISSILE EN ATLANTIQUE NECESSITANT LA CREATION DE 6 ZONES
REGLEMENTEES TEMPORAIRES ('ZRT'), DE 16 ZONES DANGEREUSES
TEMPORAIRES ('ZDT') ET FBZ ASSOCIEES.
CES 'ZRT/ZDT' SONT ACTIVEES PAR NOTAM A J-7.

PAGE 8 : REMPLACER LES COORDONNES DE LA ZONE LFDB21Z PAR :
455421N 0013949W - 455643N 0013942W - 455237N 0011542W -
455136N 0011253W - 454929N 0011048W - 453516N 0010344W -
453127N 0010358W - 452845N 0011022W - 452848N 0014111W -
453113N 0014103W - 453110N 0015559W - 453117N 0015703W -
453136N 0015801W - 453207N 0015848W - 453246N 0015919W -
453330N 0015933W - 453415N 0015928W - 453848N 0015754W -
453930N 0020815W - 454128N 0025012W - 454139N 0025119W -
454203N 0025217W - 454239N 0025301W - 454323N 0025327W -
454410N 0025333W - 454714N 0025311W - 454756N 0025257W -
454833N 0025227W - 455904N 0024055W - 455942N 0023954W -
460001N 0023837W - 460136N 0022359W - 460134N 0022236W -
455421N 0013949W

CE SUP AIP EST DISPONIBLE SUR WWW.SIA.AVIATION-CIVILE.GOUV.FR
F) SFC
G) UNL

LFBB FIR BORDEAUX

LFFA-R2429/25
DU: 13 10 2025 00:00 AU: 10 11 2026 23:59
A)LFBB
Q) LFBB / QRTCA / IV / BO / W / 000/006 / 4514N00104W004
E) CREATION D'UNE ZONE REGLEMENTEE TEMPORAIRE (ZRT) 'ZRT CESA HOURTIN' AU NORD D'HOURTIN (33) POUR
DES EVOLUTIONS D'AERONEFS SANS EQUIPAGE A BORD :
1- LIMITES LATERALES :
451250N 0010650W
451407N 0010622W
451510N 0010424W
451515N 0010255W
451455N 0010207W
451235N 0010500W
451250N 0010650W
A L'EXCLUSION DE LA RESERVE NATURELLE NATIONALE DES DUNES ET MARAIS D'HOURTIN QUI CONSERVE SON
STATUT
2- STATUT :
ZONE REGLEMENTEE TEMPORAIRE QUI SE SUBSTITUE AUX PORTIONS D'ESPACES
AERIENS AVEC LESQUELS ELLE INTERFERE.
3- CONDITIONS DE PENETRATION :
CAM ET CAG : CONTOURNEMENT OBLIGATOIRE PENDANT L'ACTIVITE REELLE SAUF
POUR :
- LES AERONEFS PARTICIPANT A L'ACTIVITE
- LES AERONEFS EFFECTUANT DES ACTIVITES MILITAIRES, DE DOUANE, DE
POLICE, DE RECHERCHE ET SAUVETAGE, DE LUTTE CONTRE LES INCENDIES OU
DU TRANSPORT MEDICAL, AYANT A INTERVENIR DANS LE CADRE DE L'EXECUTION
DE LEURS MISSIONS ET LORSQUE CELLES-CI NE PERMETTENT PAS LE

CONTOURNEMENT DE LA ZONE, APRES ACCORD DU GESTIONNAIRE
4- SERVICES RENDUS :
CAM / CAG : INFORMATION DE VOL ET ALERTE
5- INFORMATION DES USAGERS :
ACTIVITE RELLE CONNUE DE :
AQUITAINE INFO : 120.575MHZ
6- DISPOSITIONS COMPLEMENTAIRES :
LES MODALITES DE GESTION PRE-TACTIQUE ET D'ACTIVATION SONT DEFINIES
PAR PROTOCOLE
7- ORGANISME A CONTACTER :
GESTIONNAIRE ET RESPONSABLE D'ACTIVITE :
CESA DRONES : TEL 06 75 18 17 27.
F) SFC
G) 600FT AMSL

LFFA-R2431/25
DU: 13 10 2025 00:00 AU: 10 11 2026 23:59
A)LFBB
Q) LFBB / QRTCA / IV / BO / W / 000/007 / 4459N00056W002
E) CREATION D'UNE ZONE REGLEMENTEE TEMPORAIRE (ZRT) 'ZRT CESA
STE-HELENE ALPHA' A STE-HELENE (33) POUR DES EVOLUTIONS D'AERONEFS
SANS EQUIPAGE A BORD :
1- LIMITES LATERALES :
450002N 0005806W
450002N 0005445W
445922N 0005414W
445818N 0005414W
445818N 0005723W
450002N 0005806W
2- STATUT :
ZONE REGLEMENTEE TEMPORAIRE QUI SE SUBSTITUE AUX PORTIONS D'ESPACES
AERIENS AVEC LESQUELS ELLE INTERFERE.
3- CONDITIONS DE PENETRATION :
CAM ET CAG : CONTOURNEMENT OBLIGATOIRE PENDANT L'ACTIVITE REELLE SAUF
POUR :
- LES AERONEFS PARTICIPANT A L ACTIVITE
- LES AERONEFS EFFECTUANT DES ACTIVITES MILITAIRES, DE DOUANE, DE
POLICE, DE RECHERCHE ET SAUVETAGE, DE LUTTE CONTRE LES INCENDIES OU
DU TRANSPORT MEDICAL, AYANT A INTERVENIR DANS LE CADRE DE L'EXECUTION
DE LEURS MISSIONS ET LORSQUE CELLES-CI NE PERMETTENT PAS LE
CONTOURNEMENT DE LA ZONE, APRES ACCORD DU GESTIONNAIRE
4- SERVICES RENDUS :
CAM / CAG : INFORMATION DE VOL ET ALERTE
5- INFORMATION DES USAGERS :
ACTIVITE RELLE CONNUE DE :
AQUITAINE INFO 120.575MHZ
6- ORGANISME A CONTACTER :
GESTIONNAIRE ET RESPONSABLE D'ACTIVITE :
CESA DRONES : TEL. 06 75 18 17 27.
F) SFC
G) 500FT AGL

LFFA-R2432/25
DU: 13 10 2025 00:00 AU: 10 11 2026 23:59
A)LFBB
Q) LFBB / QRTCA / IV / BO / W / 005/015 / 4459N00057W002
E) CREATION D'UNE ZONE REGLEMENTEE TEMPORAIRE (ZRT) 'ZRT CESA
STE-HELENE BRAVO' A STE-HELENE (33) POUR DES EVOLUTIONS D'AERONEFS
SANS EQUIPAGE A BORD :
1- LIMITES LATERALES :
450002N 0005806W
450002N 0005554W
445818N 0005554W
445818N 0005723W
450002N 0005806W

2- STATUT :
ZONE REGLEMENTEE TEMPORAIRE QUI SE SUBSTITUE AUX PORTIONS D'ESPACES
AERIENS AVEC LESQUELS ELLE INTERFERE.
3- CONDITIONS DE PENETRATION :
CAM ET CAG : CONTOURNEMENT OBLIGATOIRE PENDANT L'ACTIVITE REELLE SAUF
POUR :
- LES AERONEFS PARTICIPANT A L'ACTIVITE
- LES AERONEFS EFFECTUANT DES ACTIVITES MILITAIRES, DE DOUANES, DE
POLICE, DE RECHERCHE ET SAUVETAGE, DE LUTTE CONTRE LES INCENDIES OU
DU TRANSPORT MEDICAL, AYANT A INTERVENIR DANS LE CADRE DE L'EXECUTION
DE LEURS MISSIONS ET LORSQUE CELLES-CI NE PERMETTENT PAS LE
CONTOURNEMENT DE LA ZONE, APRES ACCORD DU GESTIONNAIRE.
4- SERVICES RENDUS :
CAM/CAG : INFORMATION DE VOL ET ALERTE
5- INFORMATION DES USAGERS :
ACTIVITE RELLE CONNUE DE :
AQUITAINE INFO : 120.575MHZ
6- ORGANISME A CONTACTER :
GESTIONNAIRE ET RESPONSABLE D'ACTIVITE :
CESA DRONES : TEL. 06 75 18 17 27
F) 500FT AGL
G) 1500FT AMSL

LFFA-R2689/25
DU: 13 11 2025 00:00 AU: 10 11 2026 23:59
A)LFBB
Q) LFBB / QRTTT / IV / BO / W / 000/035 / 4507N00119W029
E) NOTAM TRIGGER - SUP AIP 188/25.
VOLS EN VUE ET HORS VUE D'AERONEFS SANS EQUIPAGE A BORD SUR LA COTE
ATLANTIQUE EN GIRONDE NECESSITANT LA CREATION DE 9 ZONES
REGLEMENTEES TEMPORAIRES ('ZRT').
LES 'ZRT' SONT ACTIVABLES PAR NOTAM AVEC UN PREAVIS DE 72HR.
CE SUP AIP EST DISPONIBLE SUR WWW.SIA.AVIATION-CIVILE.GOUV.FR
F) SFC
G) 3500FT AMSL

LFDK SOULAC SUR MER

LFFA-R0836/25
DU: 15 05 2025 00:00 AU: 12 05 2027 23:59
A)LFDK
Q) LFBB / QRTTT / IV / BO / AW / 000/135 / 4531N00055W018
E) NOTAM TRIGGER - SUP AIP 065/25.
VOLS D'AERONEFS SANS EQUIPAGE A BORD BASES A 'COGNAC' NECESSITANT LA CREATION DE 2 ZONES
REGLEMENTEES TEMPORAIRES 'ZRT EMS UAV' ET 'ZRT
260 LOW'.
CE SUP AIP EST DISPONIBLE SUR WWW.SIA.AVIATION-CIVILE.GOUV.FR
F) SFC
G) FL135

LFDS SARLAT DOMME

LFFA-R1846/25
DU: 18 08 2025 10:00 AU: 10 07 2026 10:00
A)LFDS
Q) LFBB / QRTTT / IV / BO / AW / 000/115 / 4438N00116E012
E) NOTAM TRIGGER - SUP AIP 138/25.
ACTIVITES SPECIFIQUES DEFENSE A 'SARLAT' ET ENTRE 'DOMME' ET
'CAHORS' NECESSITANT LA CREATION DE 4 ZONES REGLEMENTEES TEMPORAIRES ('ZRT').
LES 'ZRT' SONT ACTIVABLES PAR NOTAM A J-3.
CE SUP AIP EST DISPONIBLE SUR WWW.SIA.AVIATION-CIVILE.GOUV.FR
F) SFC
G) FL115

LFDR LA REOLE FLOUDES

LFFA-R0929/26
DU: 23 03 2026 10:33 AU: 14 04 2027 23:59
A)LFDR
Q) LFBB / QRTTT / IV / BO / AW / 030/050 / 4432N00027W018
E) NOTAM TRIGGER - SUP AIP 234/24 MODIFIE :
MODIFICATION DES ZONES LF-R204 NECESSITANT LA CREATION DE DEUX ZONES REGLEMENTEES TEMPORAIRES ('ZRT 204 L4 NEW' ET 'ZRT 204 T2 NEW').
CHANGEMENT : LES DISPOSITIONS CONTENUES DANS CE SUP AIP SONT PROROGEES JUSQU'AU 14 AVRIL 2027.
CE SUP AIP EST DISPONIBLE SUR WWW.SIA.AVIATION-CIVILE.GOUV.FR
F) 3000FT AMSL
G) 5000FT AMSL

AVERTISSEMENTS

LFBB FIR BORDEAUX

LFFA-W0017/26
DU: 07 01 2026 10:15 AU: 15 04 2026 23:59
A)LFBB
Q) LFBB / QWULW / IV / BO / W / 000/013 / 4419N00033W005
E) MODIFICATION ACTIVITE AEROMODELISME NR 9112 A 'SORE' :
HORAIRES : SR-SS
LUN-VEN : PLAFOND 500FT AGL
SAM DIM ET 06 AVR : PLAFOND 1000FT AGL
REFERENCE AIP ENR 5.5
F) SFC
G) 1000FT AGL

LFFA-W2588/25
DU: 17 11 2025 08:00 AU: 30 04 2026 18:00
A)LFBB
Q) LFBB / QWBLW / IV / M / W / 020/066 / 4448N00114W005
D) NOV 17 - MAR 28 0800-1900 EXC DEC 25 JAN 01, MAR 29 - APR 30
0700-1800 EXC APR 06
E) VOLTIGE A LA PLAGE DU 'GRAND CROHOT', RDL294/7.9NM LFCD ARP
- PSN : 444824N 0011408W
- AXE 008/188
- LONGUEUR 3000M
- INFO : AQUITAINE INFO 120.575MHZ
CAZAUX APP 119.600MHZ.
F) 2000FT AMSL
G) 6600FT AMSL

OBSTACLES

LFBC CAZAUX

LFFA-P4231/25
DU: 08 01 2026 06:00 AU: 29 05 2026 18:00
A)LFBC
Q) LFBB / QOBCE / IV / M / AE / 000/003 / 4432N00109W001
E) GRUE - RDL260/1.3NM TACAN CAA :
-PSN : 443150.5N 0010919.4W
-HAUTEUR : 200FT
-ALTITUDE AU SOMMET : 270FT
-BALISAGE : JOUR.

LFCH ARCACHON LA TESTE DE BUCH

LFFA-P1113/26

DU: 29 03 2026 06:00 AU: 08 08 2026 15:00
A)LFCH
Q) LFBB / QOBCE / IV / M / AE / 000/003 / 4436N00107W001
D) 0600-1500
E) GRUE MOBILE ERIGEE A LA TESTE DE BUCH : RDL 330/0.46NM ARP LFCH
PSN : 443610.43N 0010715.04W
HAUTEUR : 164FT
ALT SOMMET : 209FT
BALISAGE : JOUR ET NUIT

LFDY BORDEAUX YVRAC

LFFA-P0931/26

DU: 11 03 2026 09:11 AU: 01 04 2026 23:59
A)LFDY
Q) LFBB / QOLAS / IV / M / AE / 000/011 / 4449N00030W001
E) BALISAGE PYLONE 33005 HORS SERVICE - RDL093/8.9NM LFBD :
-PSN : 444911N 0003019W
-ALTITUDE AU SOMMET : 1041FT
-HAUTEUR : 818FT.

MÉTÉO TRAJET

Date et Heure de production (UTC)
29-03-2026 20:13

Date et heure de départ (UTC)
30-03-2026 10:00

Départ
LFBX

Destination
LFBD

Aérodromes de dégagement ou survolés
-

Zone de couverture
FRANCE

Niveau de carte (FL)
100

Rayon et demi-couloir (en NM)
45

OPMET (SOURCE MÉTÉO FRANCE)

LFBC CAZAUX

METAR

METAR LFBC 292000Z AUTO 35005KT 320V020 CAVOK 08/03 Q1035=

SIGMET

LFBB SIGMET U14 VALID 292000/300000 LFPW-LFBB BORDEAUX FIR/UIR SEV TURB FCST WI N4215 E00230 - N4300 W00130 - N4315 W00100 - N4230 E00215 - N4500 E00245 - N4215 E00230 SFC/FL120STNR NC=

SIGMET

LFBB SIGMET U13 VALID 292000/300000 LFPW-LFBB BORDEAUX FIR/UIR SEV TURB FCST WI N4215 E00230 - N4300 W00130 - N4315 W00100 - N4230 E00215 - N4500 E00245 - N4215 E00230 SFC/FL120STNR NC=

SIGMET

LFBB SIGMET U12 VALID 291800/292100 LFPW-LFBB BORDEAUX FIR/UIR SEV TURB FCST SE OF LINE N4245 E00015 - N4415E00245 FL220/380 MOV SE 20KT NC=

LFBG COGNAC CHATEAUBERNARD

METAR

METAR LFBG 292000Z AUTO 30007KT CAVOK 09/03 Q1033=

SIGMET

LFBB SIGMET U14 VALID 292000/300000 LFPW-LFBB BORDEAUX FIR/UIR SEV TURB FCST WI N4215 E00230 - N4300 W00130 - N4315 W00100 - N4230 E00215 - N4500 E00245 - N4215 E00230 SFC/FL120STNR NC=

SIGMET

LFBB SIGMET U13 VALID 292000/300000 LFPW-LFBB BORDEAUX FIR/UIR SEV TURB FCST WI N4215 E00230 - N4300 W00130 - N4315 W00100 - N4230 E00215 - N4500 E00245 - N4215 E00230 SFC/FL120STNR NC=

SIGMET

LFBB SIGMET U12 VALID 291800/292100 LFPW-LFBB BORDEAUX FIR/UIR SEV TURB FCST SE OF LINE N4245 E00015 - N4415E00245 FL220/380 MOV SE 20KT NC=

LFBE BERGERAC ROUMANIERE

METAR

METAR LFBE 292000Z AUTO 24005KT CAVOK 06/M00 Q1033 NOSIG=

TAFL

TAF AMD LFBE 292003Z 2920/3012 CNL=

SIGMET

LFBB SIGMET U14 VALID 292000/300000 LFPW-LFBB BORDEAUX FIR/UIR SEV TURB FCST WI N4215 E00230 - N4300 W00130 - N4315 W00100 - N4230 E00215 - N4500 E00245 - N4215 E00230 SFC/FL120STNR NC=

SIGMET

LFBB SIGMET U13 VALID 292000/300000 LFPW-LFBB BORDEAUX FIR/UIR SEV TURB FCST WI N4215 E00230 - N4300 W00130 - N4315 W00100 - N4230 E00215 - N4500 E00245 - N4215 E00230 SFC/FL120STNR NC=

SIGMET

LFBB SIGMET U12 VALID 291800/292100 LFPW-LFBB BORDEAUX FIR/UIR SEV TURB FCST SE OF LINE N4245 E00015 - N4415E00245 FL220/380 MOV SE 20KT NC=

LFBD BORDEAUX MERIGNAC

METAR

METAR LFBD 292000Z AUTO 31006KT CAVOK 08/03 Q1034 NOSIG=

TAFL

TAF LFBD 291700Z 2918/3024 35010KT CAVOK TX14/3014Z TN05/3001Z BECMG2918/2920 30005KT BECMG 3004/3006 25010KT BKN015 TEMPO 3008/3012 3000 -RADZ OVC005 PROB40 TEMPO 3009/3011 1500 RA OVC003 BECMG 3012/301431010KT=

SIGMET

LFBB SIGMET U14 VALID 292000/300000 LFPW-LFBB BORDEAUX FIR/UIR SEV TURB FCST WI N4215 E00230 - N4300 W00130 - N4315 W00100 - N4230 E00215 - N4500 E00245 - N4215 E00230 SFC/FL120STNR NC=

SIGMET

LFBB SIGMET U13 VALID 292000/300000 LFPW-LFBB BORDEAUX FIR/UIR SEV TURB FCST WI N4215 E00230 - N4300 W00130 - N4315 W00100 - N4230 E00215 - N4500 E00245 - N4215 E00230 SFC/FL120STNR NC=

SIGMET

LFBB SIGMET U12 VALID 291800/292100 LFPW-LFBB BORDEAUX FIR/UIR SEV TURB FCST SE OF LINE N4245 E00015 - N4415E00245 FL220/380 MOV SE 20KT NC=

LFBL LIMOGES BELLEGARDE

METAR

METAR LFBL 292000Z AUTO 30005KT CAVOK 05/M02 Q1031 NOSIG=

TAFL

TAF LFBL 291700Z 2918/3018 01010KT CAVOK BECMG 2918/2920 VRB03KTBECMG 3004/3006 25005KT 3000 BR BKN005 TEMPO 3006/3011 0800 FG VV///BECMG 3011/3013 32010KT 9999 NSW BKN035 TEMPO 3013/3015 -SHRA BKN010BKN015TCU=

SIGMET

LFBB SIGMET U14 VALID 292000/300000 LFPW-LFBB BORDEAUX FIR/UIR SEV TURB FCST WI N4215 E00230 - N4300 W00130 - N4315 W00100 - N4230 E00215 - N4500 E00245 - N4215 E00230 SFC/FL120STNR NC=

SIGMET

LFBB SIGMET U13 VALID 292000/300000 LFPW-LFBB BORDEAUX FIR/UIR SEV TURB FCST WI N4215 E00230 - N4300 W00130 - N4315 W00100 - N4230 E00215 - N4500 E00245 - N4215 E00230 SFC/FL120STNR NC=

SIGMET

LFBB SIGMET U12 VALID 291800/292100 LFPW-LFBB BORDEAUX FIR/UIR SEV TURB FCST SE OF LINE N4245 E00015 - N4415E00245 FL220/380 MOV SE 20KT NC=

LFBS BISCARROSSE PARENTIS

METAR

METAR LFBS 291800Z AUTO 34012KT 320V040 9999 FEW035 10/03 Q1034=

SIGMET

LFBB SIGMET U14 VALID 292000/300000 LFPW-LFBB BORDEAUX FIR/UIR SEV TURB FCST WI N4215 E00230 - N4300 W00130 - N4315 W00100 - N4230 E00215 - N4500 E00245 - N4215 E00230 SFC/FL120STNR NC=

SIGMET

LFBB SIGMET U13 VALID 292000/300000 LFPW-LFBB BORDEAUX FIR/UIR SEV TURB FCST WI N4215 E00230 - N4300 W00130 - N4315 W00100 - N4230 E00215 - N4500 E00245 - N4215 E00230 SFC/FL120STNR NC=

SIGMET

LFBB SIGMET U12 VALID 291800/292100 LFPW-LFBB BORDEAUX FIR/UIR SEV TURB FCST SE OF LINE N4245 E00015 - N4415E00245 FL220/380 MOV SE 20KT NC=

LFBU ANGOULEME BRIE CHAMPNIERS

METAR

METAR LFBU 292000Z AUTO 29004KT CAVOK 07/00 Q1033 BECMG 35010KT=

TAFL

TAF LFBU 291700Z 2918/3018 35010KT CAVOK BECMG 3004/3006 24010KT 3000 -RA BKN005 OVC012 TEMPO 3007/3010 1500 RA BKN002 BECMG 3010/301233010KT 9999 NSW BKN040 TEMPO 3012/3014 34015G25KT -SHRA BKN040TCU=

SIGMET

LFBB SIGMET U14 VALID 292000/300000 LFPW-LFBB BORDEAUX FIR/UIR SEV TURB FCST WI N4215 E00230 - N4300 W00130 - N4315 W00100 - N4230 E00215 - N4500 E00245 - N4215 E00230 SFC/FL120STNR NC=

SIGMET

LFBB SIGMET U13 VALID 292000/300000 LFPW-LFBB BORDEAUX FIR/UIR SEV TURB FCST WI N4215 E00230 - N4300 W00130 - N4315 W00100 - N4230 E00215 - N4500 E00245 - N4215 E00230 SFC/FL120STNR NC=

SIGMET

LFBB SIGMET U12 VALID 291800/292100 LFPW-LFBB BORDEAUX FIR/UIR SEV TURB FCST SE OF LINE N4245 E00015 - N4415E00245 FL220/380 MOV SE 20KT NC=

LFBX PERIGUEUX BASSILLAC

METAR

METAR LFBX 292000Z AUTO VRB01KT CAVOK 04/M01 Q1032=

SIGMET

LFBB SIGMET U14 VALID 292000/300000 LFPW-LFBB BORDEAUX FIR/UIR SEV TURB FCST WI N4215 E00230 - N4300 W00130 - N4315 W00100 - N4230 E00215 - N4500 E00245 - N4215 E00230 SFC/FL120STNR NC=

SIGMET

LFBB SIGMET U13 VALID 292000/300000 LFPW-LFBB BORDEAUX FIR/UIR SEV TURB FCST WI N4215 E00230 - N4300 W00130 - N4315 W00100 - N4230 E00215 - N4500 E00245 - N4215 E00230 SFC/FL120STNR NC=

SIGMET

LFBB SIGMET U12 VALID 291800/292100 LFPW-LFBB BORDEAUX FIR/UIR SEV TURB FCST SE OF LINE N4245 E00015 - N4415E00245 FL220/380 MOV SE 20KT NC=

LFSL BRIVE SOUILLAC

METAR

METAR LFSL 292000Z AUTO 31005KT CAVOK 06/M02 Q1031 NOSIG=

TAFC

TAF AMD LFSL 292003Z 2920/2924 CNL=

SIGMET

LFBB SIGMET U14 VALID 292000/300000 LFPW-LFBB BORDEAUX FIR/UIR SEV TURB FCST WI N4215 E00230 - N4300 W00130 - N4315 W00100 - N4230 E00215 - N4500 E00245 - N4215 E00230 SFC/FL120STNR NC=

SIGMET

LFBB SIGMET U13 VALID 292000/300000 LFPW-LFBB BORDEAUX FIR/UIR SEV TURB FCST WI N4215 E00230 - N4300 W00130 - N4315 W00100 - N4230 E00215 - N4500 E00245 - N4215 E00230 SFC/FL120STNR NC=

SIGMET

LFBB SIGMET U12 VALID 291800/292100 LFPW-LFBB BORDEAUX FIR/UIR SEV TURB FCST SE OF LINE N4245 E00015 - N4415E00245 FL220/380 MOV SE 20KT NC=

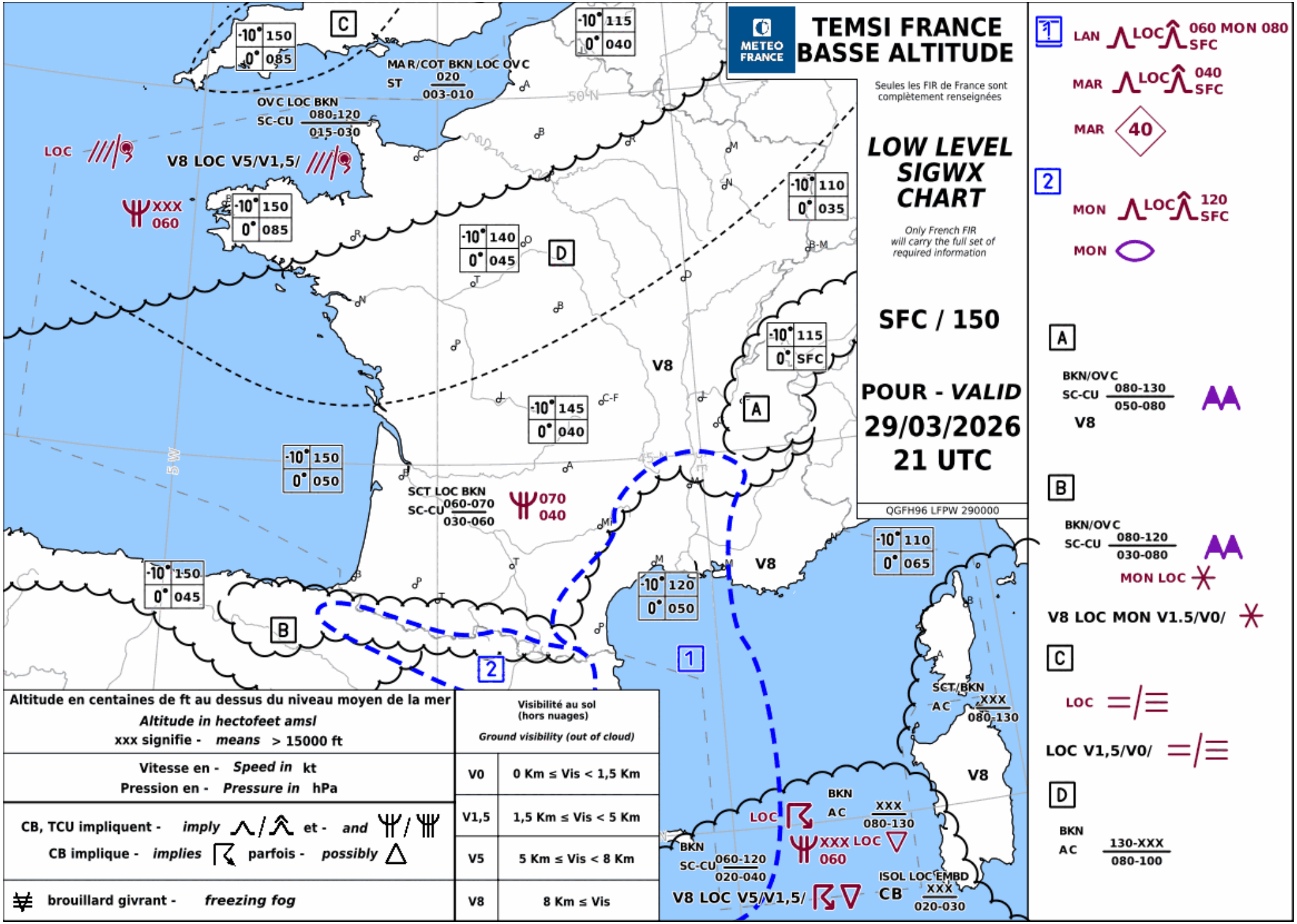
METEO FRANCE
TEMSI FRANCE
BASSE ALTITUDE
Seules les FIR de France sont complètement renseignées
LOW LEVEL SIGWX CHART
Only French FIR will carry the full set of required information
SFC / 150
POUR - VALID
29/03/2026
21 UTC
QGFH96 LFPW 290000
C
MA R/COT BKN LOC OVC
ST 020 / 003-010
OVC LOC BKN
SC-CU 080-120 / 015-030
LOC
V8 LOC V5/V1,5/
XXX 060
-10° 150 / 0° 085
-10° 115 / 0° 040
-10° 110 / 0° 035
-10° 140 / 0° 045
D
-10° 115 / 0° SFC
V8
-10° 145 / 0° 040
A
-10° 150 / 0° 050
SCT LOC BKN
SC-CU 060-070 / 030-060
070 040
-10° 110 / 0° 065
-10° 120 / 0° 050
-10° 150 / 0° 045
B
1
2
SCT/BKN
AC XXX / 080-130
BKN
AC XXX / 080-130
LOC
XXX 060 LOC
BKN
SC-CU 060-120 / 020-040
V8 LOC V5/V1,5/
ISOL LOC EMBD
CB XXX / 020-030
1
LAN LOC 060 MON 080 SFC
MAR LOC 040 SFC
MAR 40
2
MON LOC 120 SFC
MON
A
BKN/OVC
SC-CU 080-130 / 050-080
V8
B
BKN/OVC
SC-CU 080-120 / 030-080
MON LOC
V8 LOC MON V1.5/V0/
C
LOC
LOC V1,5/V0/
D
BKN
AC 130-XXX / 080-100
Altitude en centaines de ft au dessus du niveau moyen de la mer
Altitude in hectofeet amsl
xxx signifie - means > 15000 ft
Vitesse en - Speed in kt
Pression en - Pressure in hPa
CB, TCU impliquent - imply et - and
CB implique - implies parfois - possibly
brouillard givrant - freezing fog
Visibilité au sol (hors nuages)
Ground visibility (out of cloud)
V0 0 Km ≤ Vis < 1,5 Km
V1,5 1,5 Km ≤ Vis < 5 Km
V5 5 Km ≤ Vis < 8 Km
V8 8 Km ≤ Vis

DATA FROM METEO-FRANCE
WIND (kt) / TEMP (C)
TEMPERATURE NEGATIVE UNLESS PREFIXED BY +
FL020 (950hpa)
VALID 21 UTC ON 29 MAR 2026

BASED ON 12 UTC DATA ON 29 MAR 2026



DATA FROM METEO-FRANCE
WIND (kt) / TEMP (C)
TEMPERATURE NEGATIVE UNLESS PREFIXED BY +
FL050 (850hpa)
VALID 21 UTC ON 29 MAR 2026

BASED ON 12 UTC DATA ON 29 MAR 2026

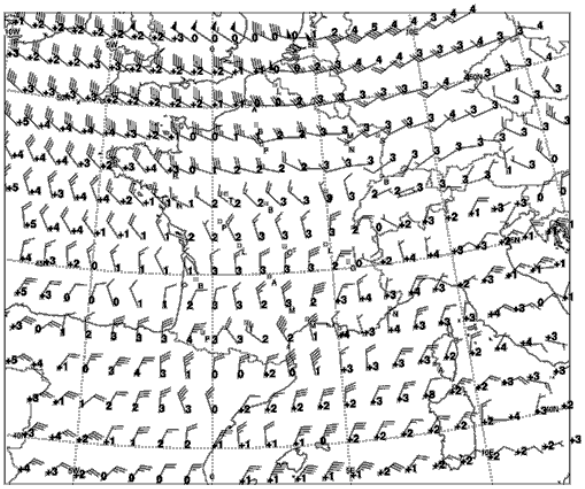

DATA FROM METEO-FRANCE
WIND (kt) / TEMP (C)
TEMPERATURE NEGATIVE UNLESS PREFIXED BY +
FL100 (700hpa)
VALID 21 UTC ON 29 MAR 2026

BASED ON 12 UTC DATA ON 29 MAR 2026

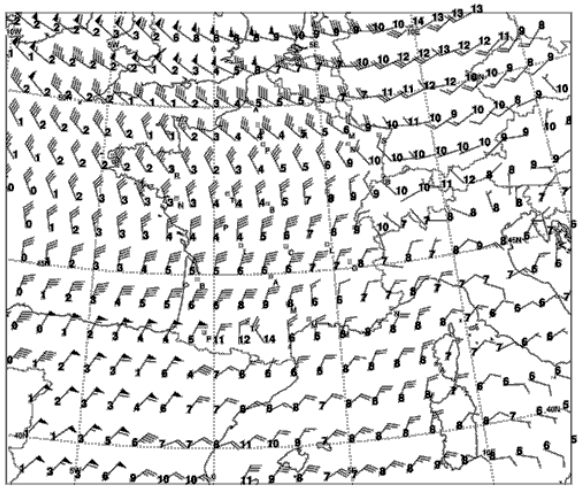

DATA FROM METEO-FRANCE
WIND (kt) / TEMP (C)
TEMPERATURE NEGATIVE UNLESS PREFIXED BY +
FL020 (950hpa)
VALID 00 UTC ON 30 MAR 2026

BASED ON 12 UTC DATA ON 29 MAR 2026

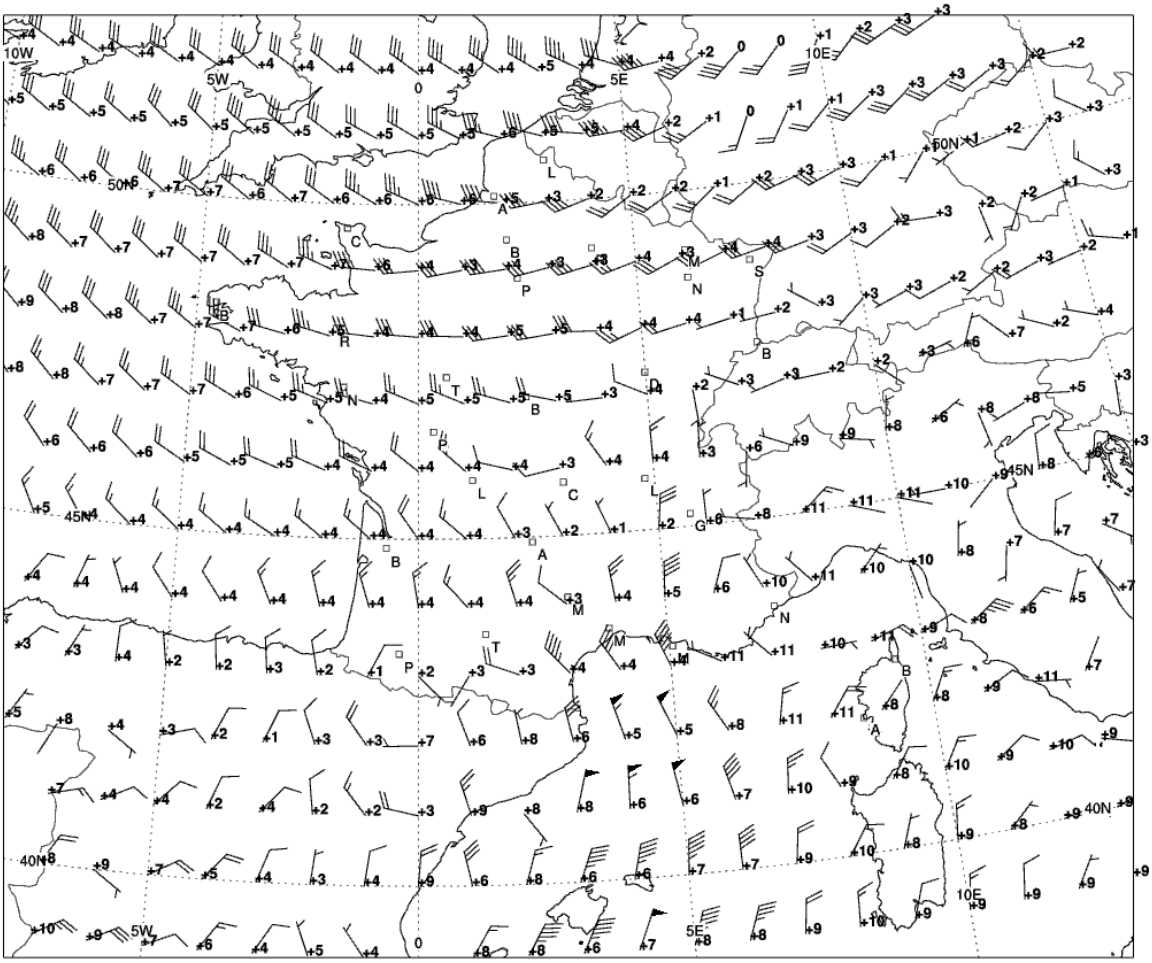

DATA FROM METEO-FRANCE
WIND (kt) / TEMP (C)
TEMPERATURE NEGATIVE UNLESS PREFIXED BY +
FL050 (850hpa)
VALID 00 UTC ON 30 MAR 2026

BASED ON 12 UTC DATA ON 29 MAR 2026

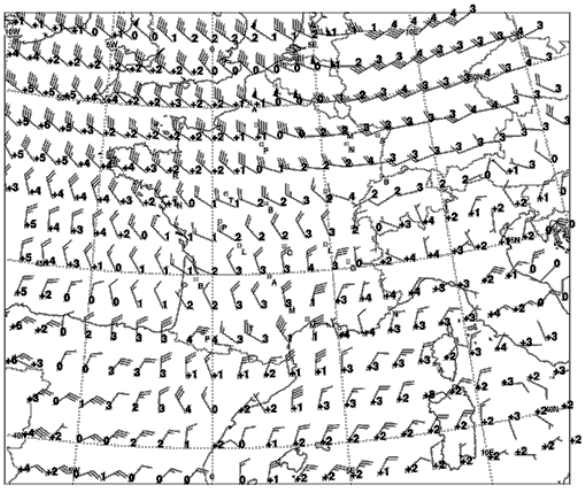

DATA FROM METEO-FRANCE
WIND (kt) / TEMP (C)
TEMPERATURE NEGATIVE UNLESS PREFIXED BY +
FL100 (700hpa)
VALID 00 UTC ON 30 MAR 2026

BASED ON 12 UTC DATA ON 29 MAR 2026

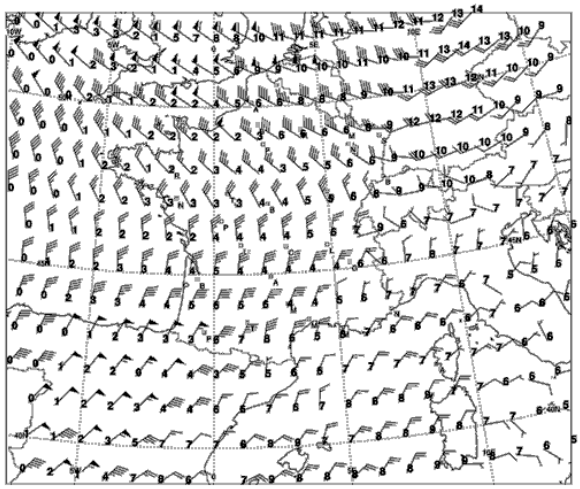

DATA FROM METEO-FRANCE
WIND (kt) / TEMP (C)
TEMPERATURE NEGATIVE UNLESS PREFIXED BY +
FL020 (950hpa)
VALID 03 UTC ON 30 MAR 2026

BASED ON 12 UTC DATA ON 29 MAR 2026

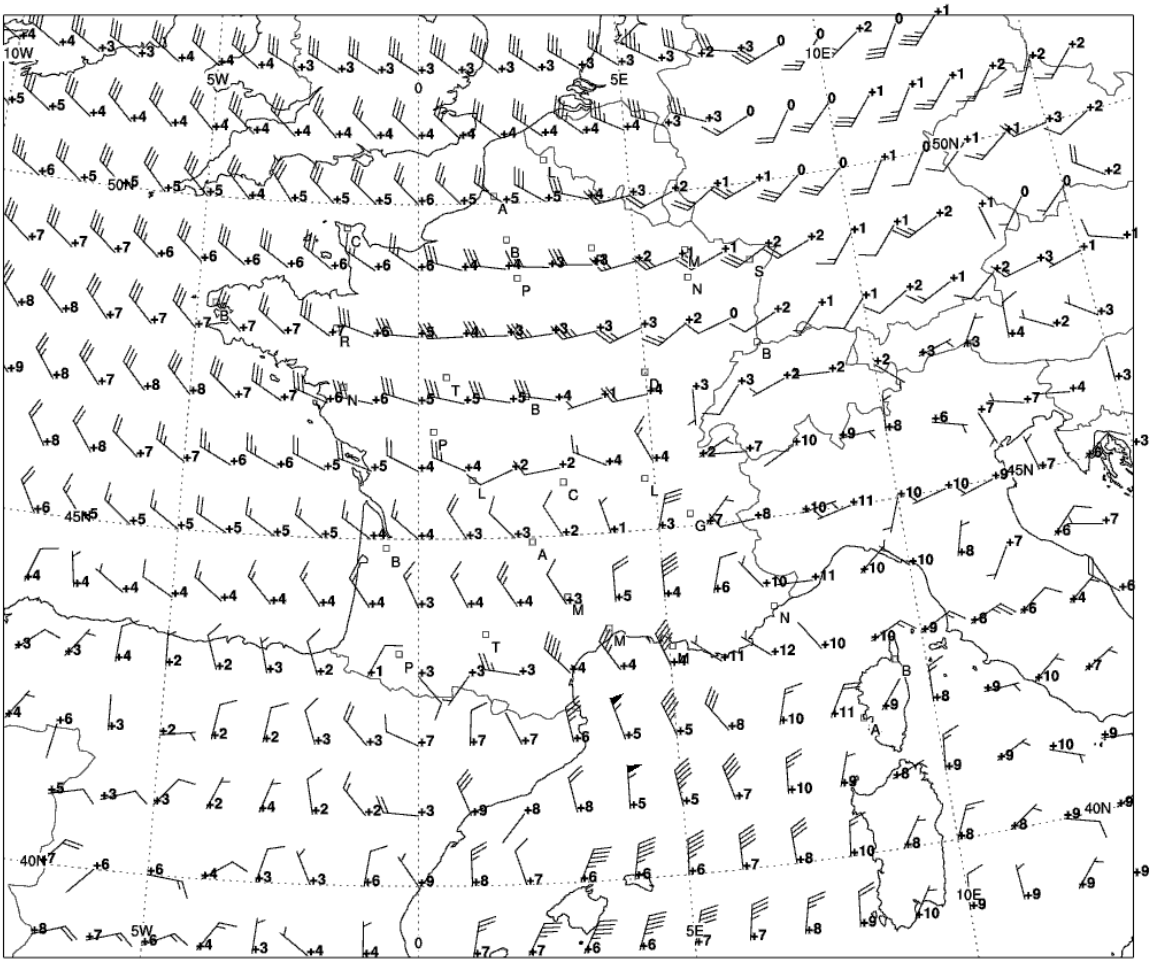

DATA FROM METEO-FRANCE
WIND (kt) / TEMP (C)
TEMPERATURE NEGATIVE UNLESS PREFIXED BY +
FL050 (850hpa)
VALID 03 UTC ON 30 MAR 2026

BASED ON 12 UTC DATA ON 29 MAR 2026



DATA FROM METEO-FRANCE
WIND (kt) / TEMP (C)
TEMPERATURE NEGATIVE UNLESS PREFIXED BY +
FL100 (700hpa)
VALID 03 UTC ON 30 MAR 2026
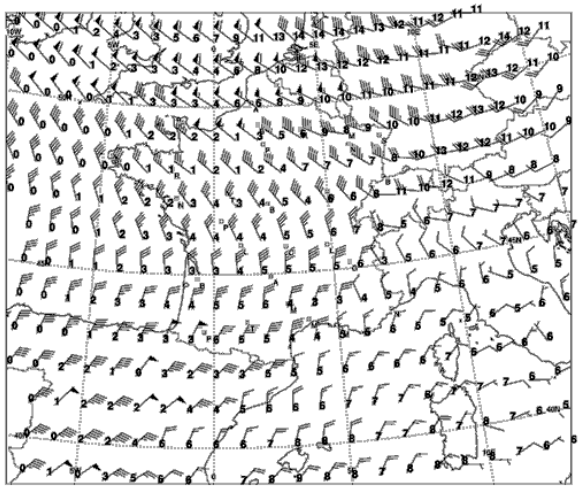
BASED ON 12 UTC DATA ON 29 MAR 2026